공 고

◈ 서울특별시공고 제2021-3211호

토지거래계약허가구역 지정 공고

「부동산 거래신고 등에 관한 법률」 제10조에 따라 다음과 같이 토지거래허가구역을 지정 공고합니다.

2021년 12월 28일
서 울 특 별 시 장

1. 허가구역 지정 대상지역

대상지역			면적(㎡)	비 고
합 계			1,256,197	
서울특별시	종로구	창신동 23번지 일대	41,261	주택재개발
		숭인동 56번지 일대	43,093	
	용산구	청파동1가89-18번지 일대	83,788	
	성동구	마장동 382번지 일대	18,749	
	동대문구	청량리동 19번지 일대	27,981	
	중랑구	면목동 69-14 일대	58,540	
	성북구	하월곡동 70-1번지 일대	79,756	
	강북구	수유동 170번지 일대	12,124	
	도봉구	쌍문동 724번지 일대	10,619	
	노원구	상계동 154-3번지 일대	192,670	
	은평구	불광동 600 일대	13,004	
	서대문구	홍은동 8-400번지 일대	71,860	
	마포구	공덕동 11-24번지 일대	82,320	
	양천구	신월동 913~976번지	115,699	
	강서구	방화동 589-13번지 일대	34,906	
	구로구	가리봉동 87-177 일대	37,672	
	금천구	시흥동 810번지 일대	38,859	

대상지역			면적(㎡)	비 고
	영등포구	당산동6가 104번지 일대	31,299	
	동작구	상도동 244번지 일대	50,142	
	관악구	신림동 675번지 일대	75,600	
	송파구	마천동 93-5번지 일대	106,101	
	강동구	천호동 461-31번지 일대	30,154	

2. 허가구역 지정기간 : 2022년 1월 2일부터 2023년 1월 1일까지

3. 토지거래계약에 관한 허가를 받아야 하는 면적

용 도 지 역		면 적
도시지역	주거지역	18㎡ 초과
	상업지역	20㎡ 초과
	공업지역	66㎡ 초과
	녹지지역	10㎡ 초과
	용도지역의 지정이 없는 곳	9㎡ 초과

4. 허가구역 지정 토지조서 : 붙임1 참조
※「공간정보의 구축 및 관리 등에 관한 법률」에 따른 토지이동 및 등록사항정정 토지가 반영되지 않을 수 있음으로 최종조서는 허가구역 지정도면(구역 설정)을 기준

5. 허가구역 지정 지형도 : 붙임2 참조
※ 토지e음(http://www.eum.go.kr)에서 토지거래허가구역 세부정보를 확인

붙임1	토지거래허가구역 지형도면

< 서울특별시 종로구 창신동 23번지 일대 토지거래계약 허가구역 지형도면 >

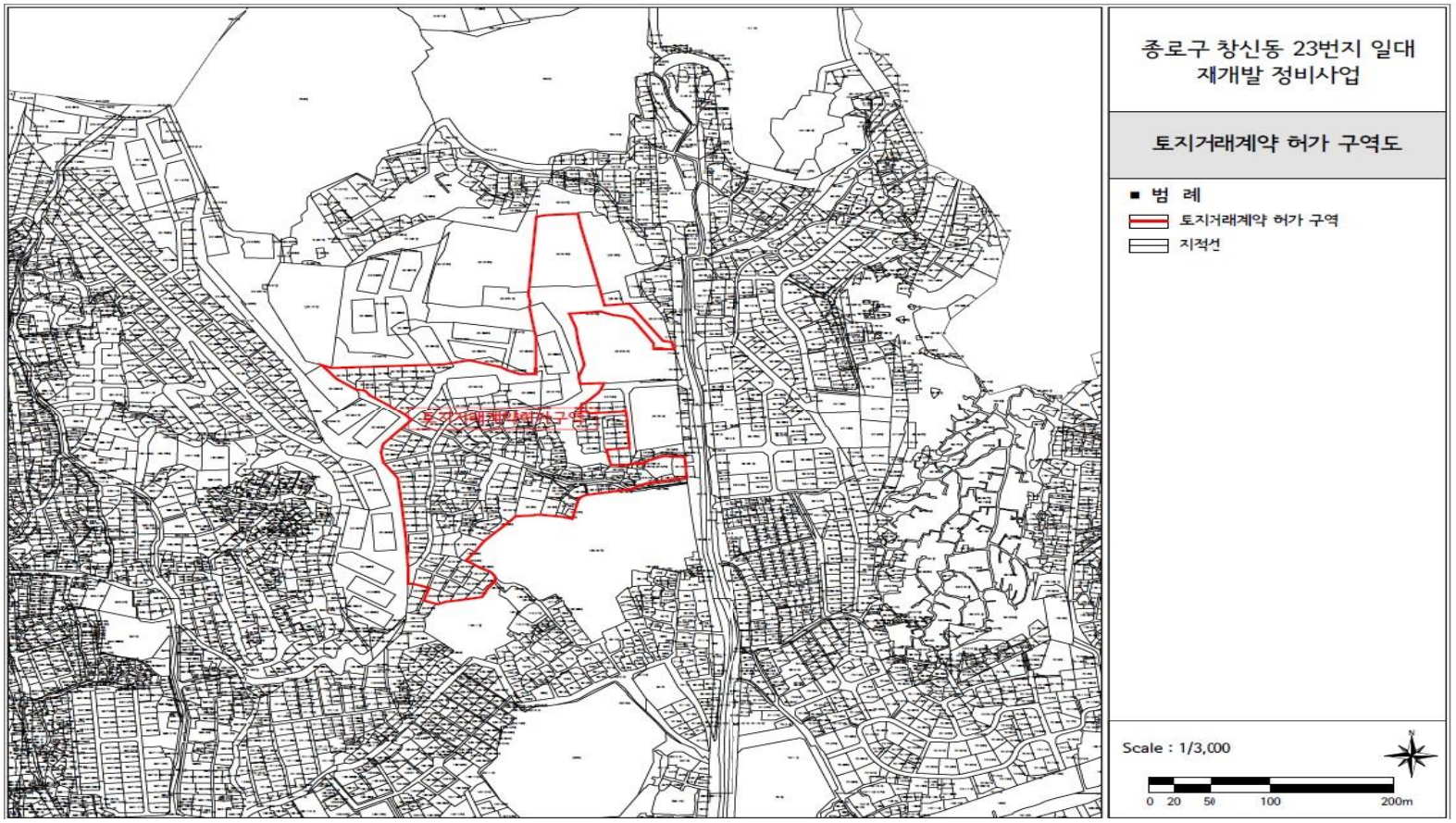

< 서울특별시 종로구 숭인동 56번지 일대 토지거래계약 허가구역 지형도면 >

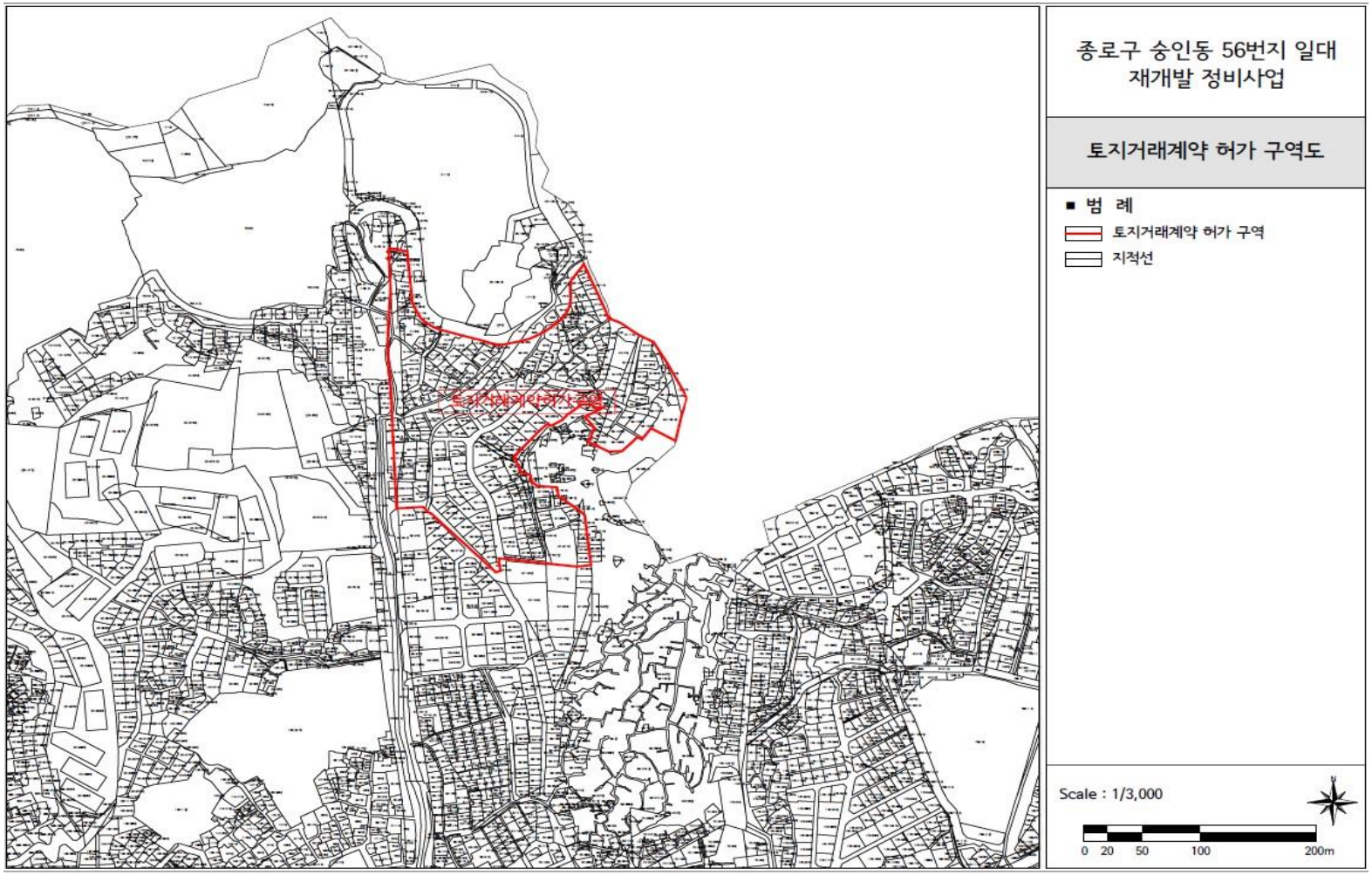

< 서울특별시 용산구 청파동1가 89-18번지 일대 토지거래계약 허가구역 지형도면 >

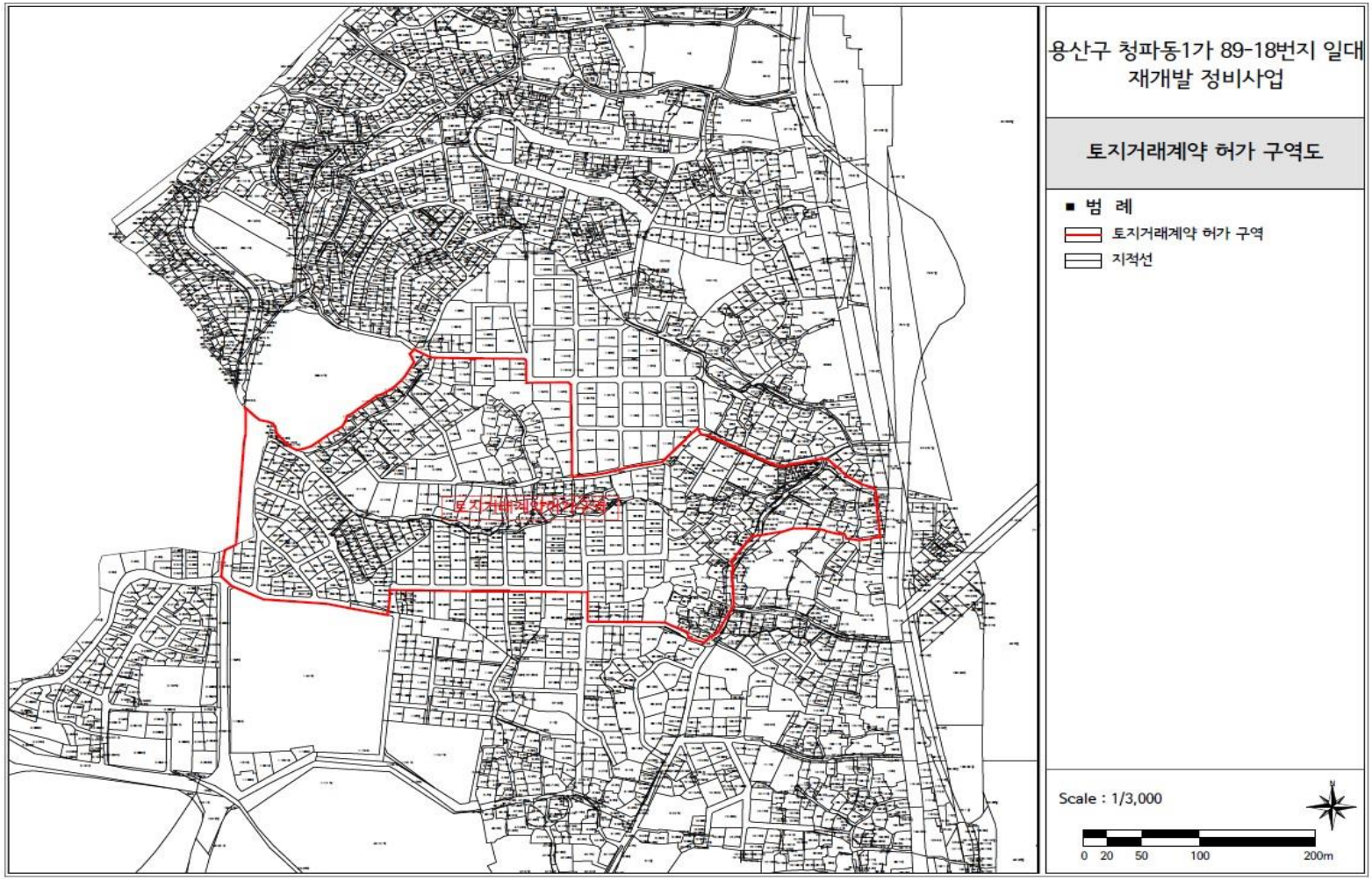

< 서울특별시 성동구 마장동 381번지 일대 토지거래계약 허가구역 지형도면 >

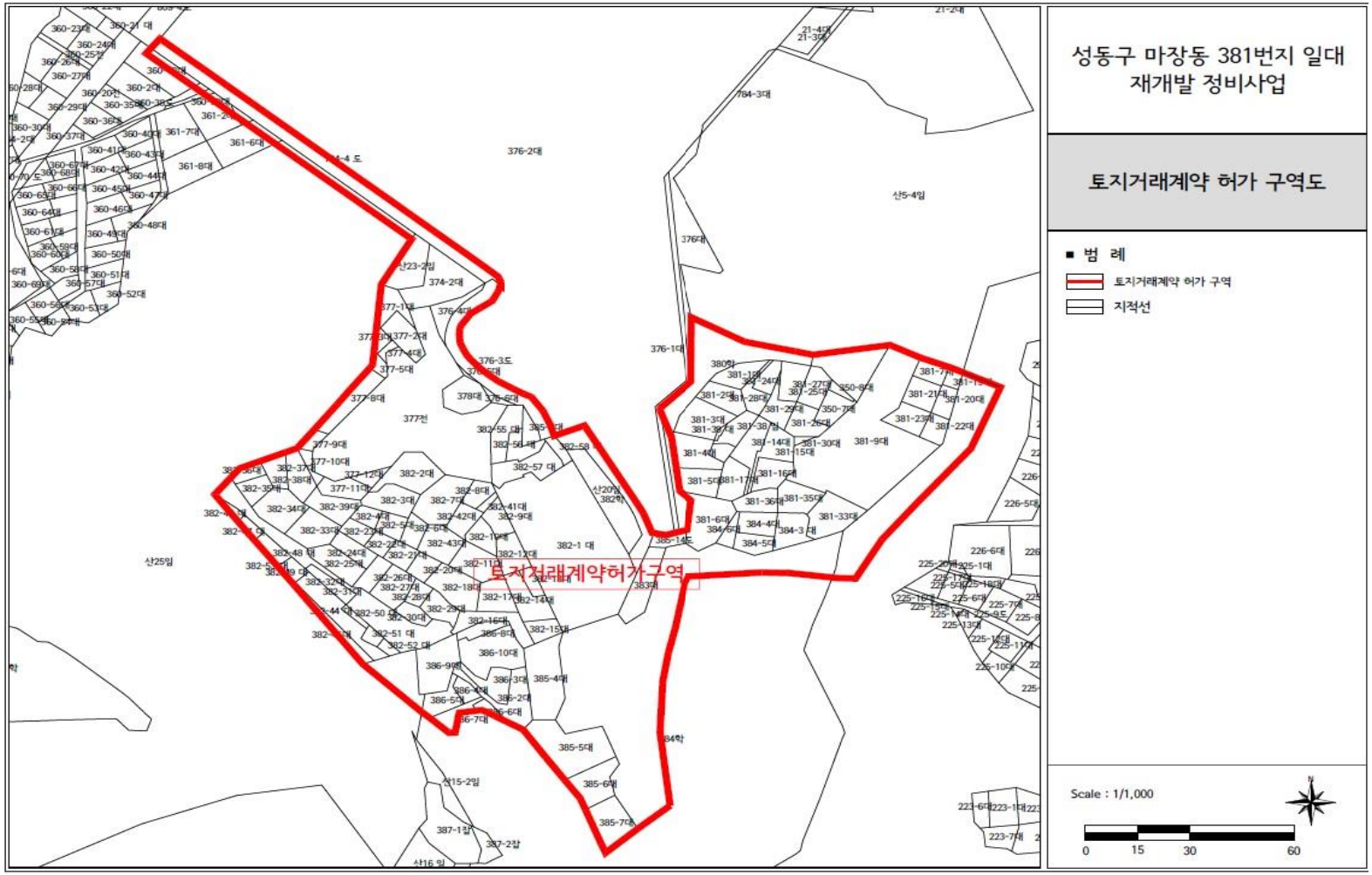

< 서울특별시 동대문구 청량리동 19번지 일대 토지거래계약 허가구역 지형도면 >

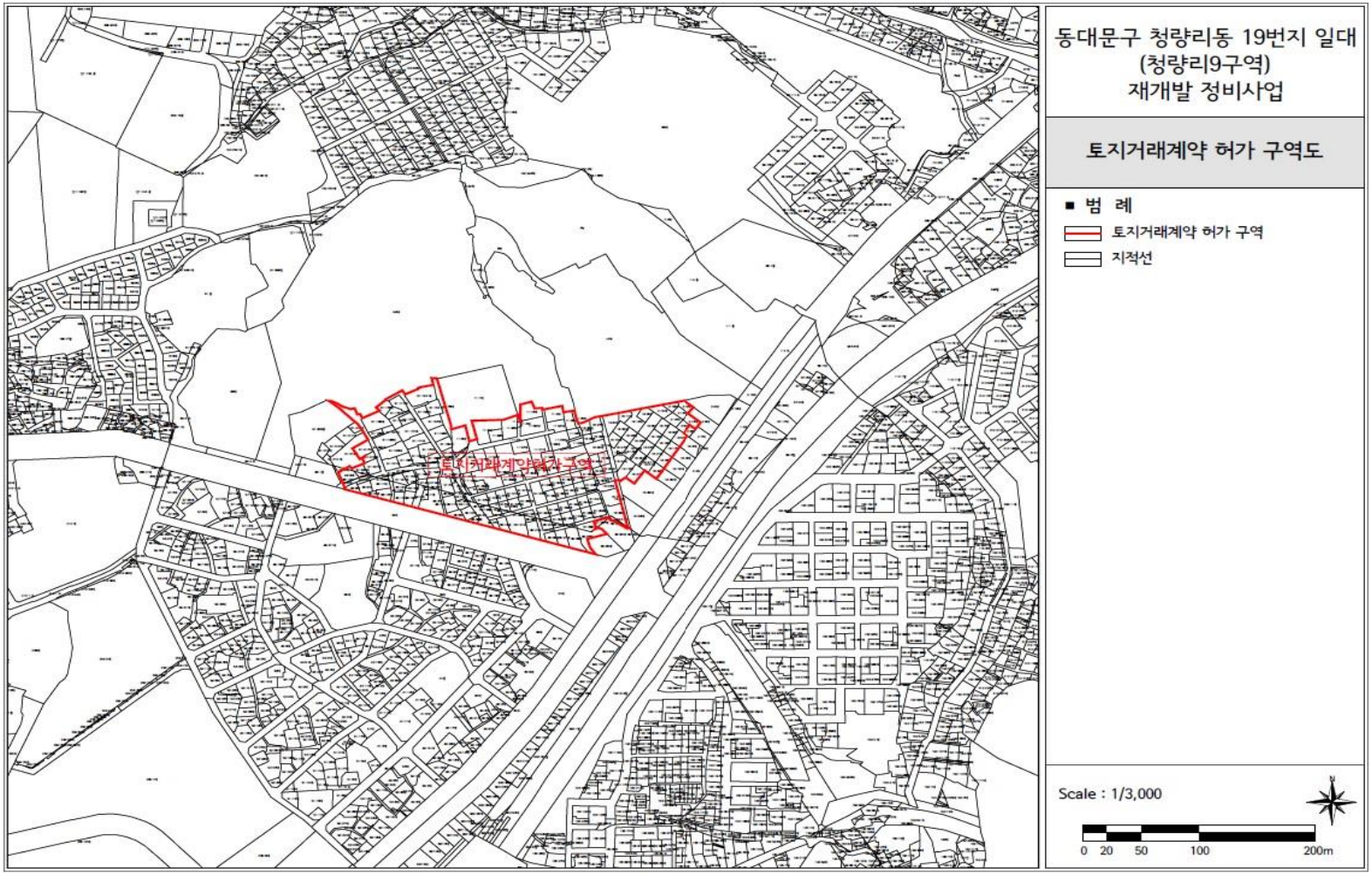

< 서울특별시 중랑구 면목동 69-14번지 일대 토지거래계약 허가구역 지형도면 >

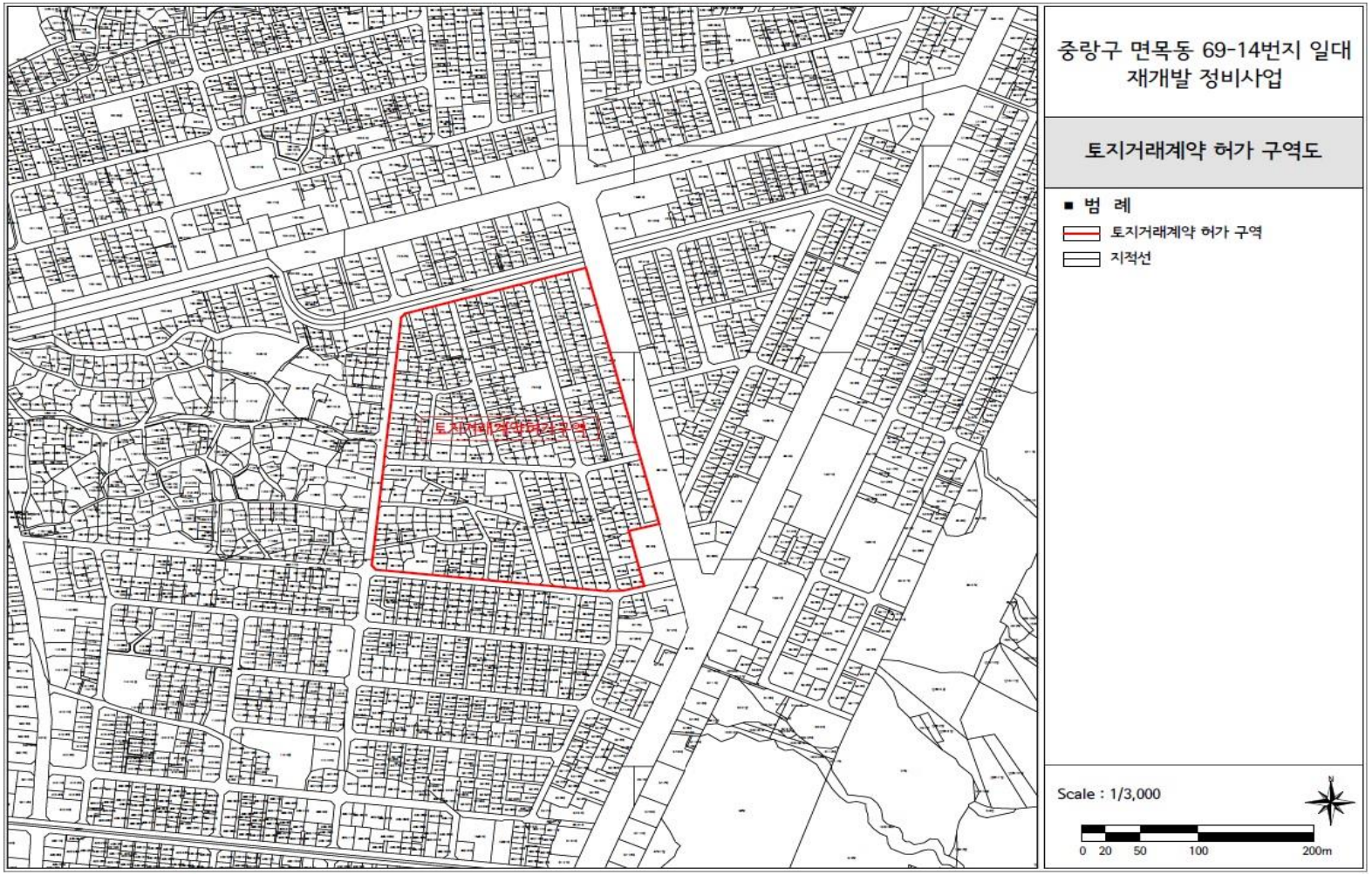

< 서울특별시 성북구 하월곡동 70-1번지 일대 토지거래계약 허가구역 지형도면 >

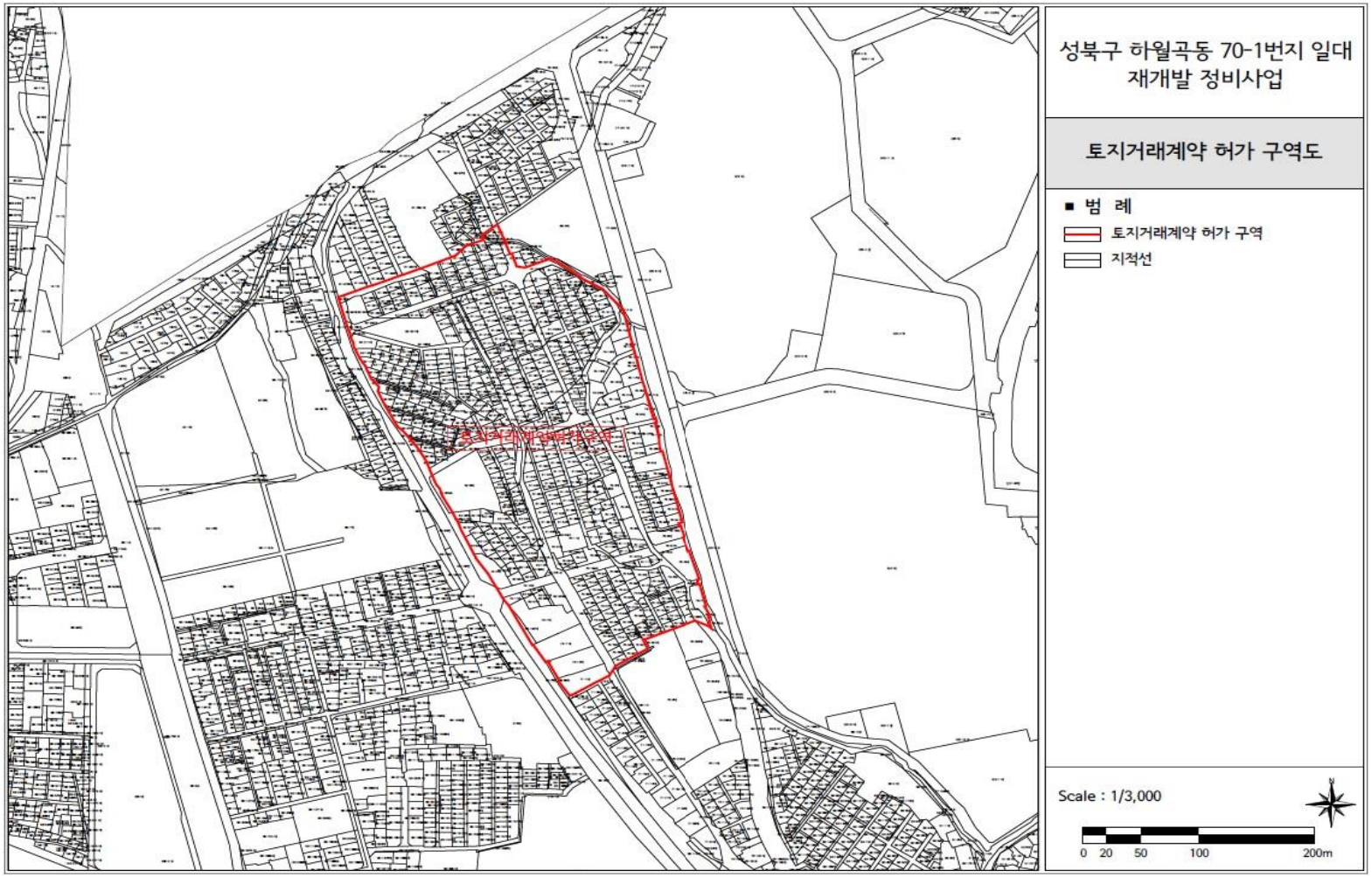

< 서울특별시 강북구 수유동 170-1번지 일대 토지거래계약 허가구역 지형도면 >

< 서울특별시 도봉구 쌍문동 724번지 일대 토지거래계약 허가구역 지형도면 >

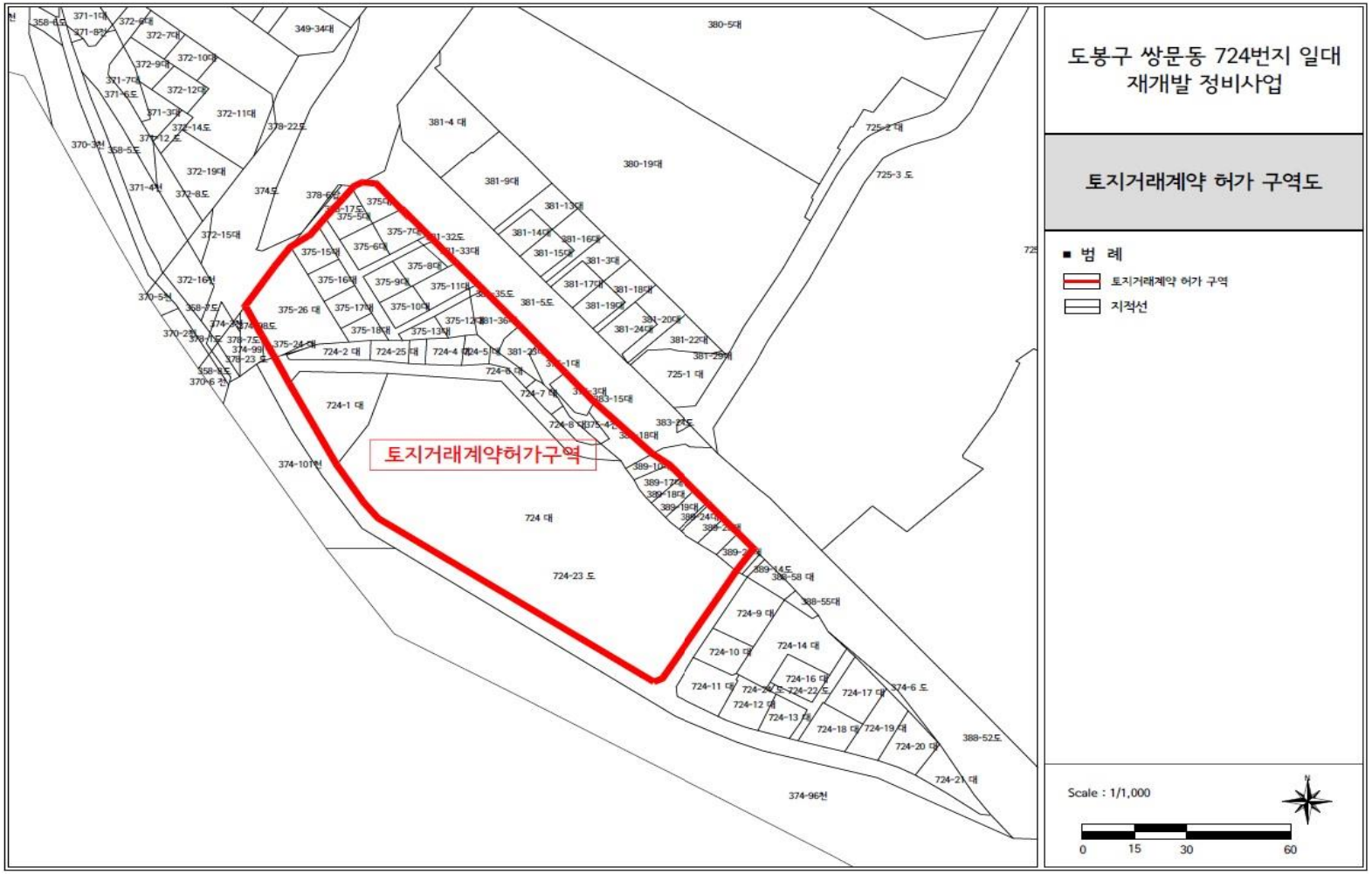

< 서울특별시 노원구 상계동 135번지 일대 토지거래계약 허가구역 지형도면 >

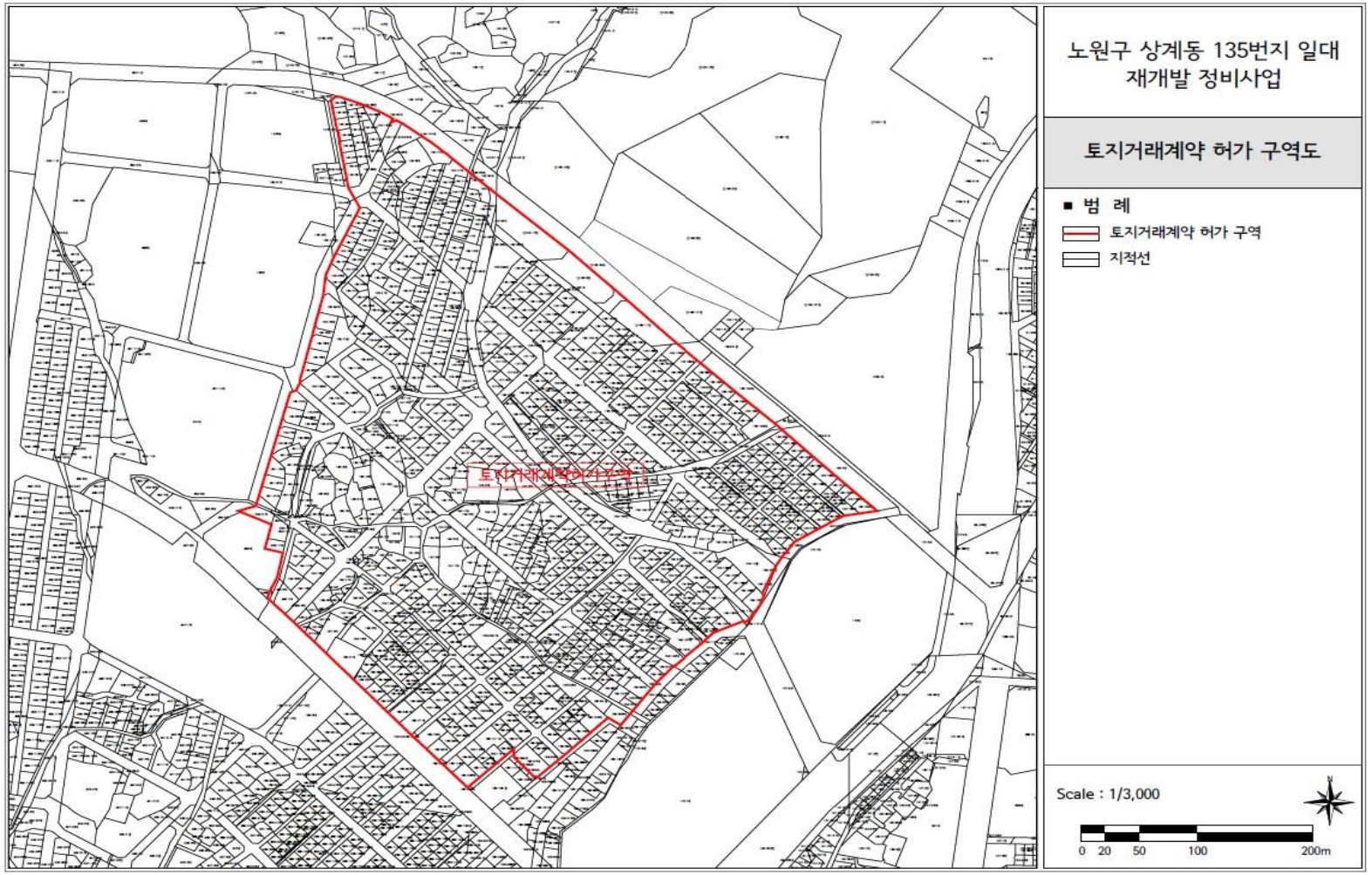

< 서울특별시 은평구 불광동 600번지 일대 토지거래계약 허가구역 지형도면 >

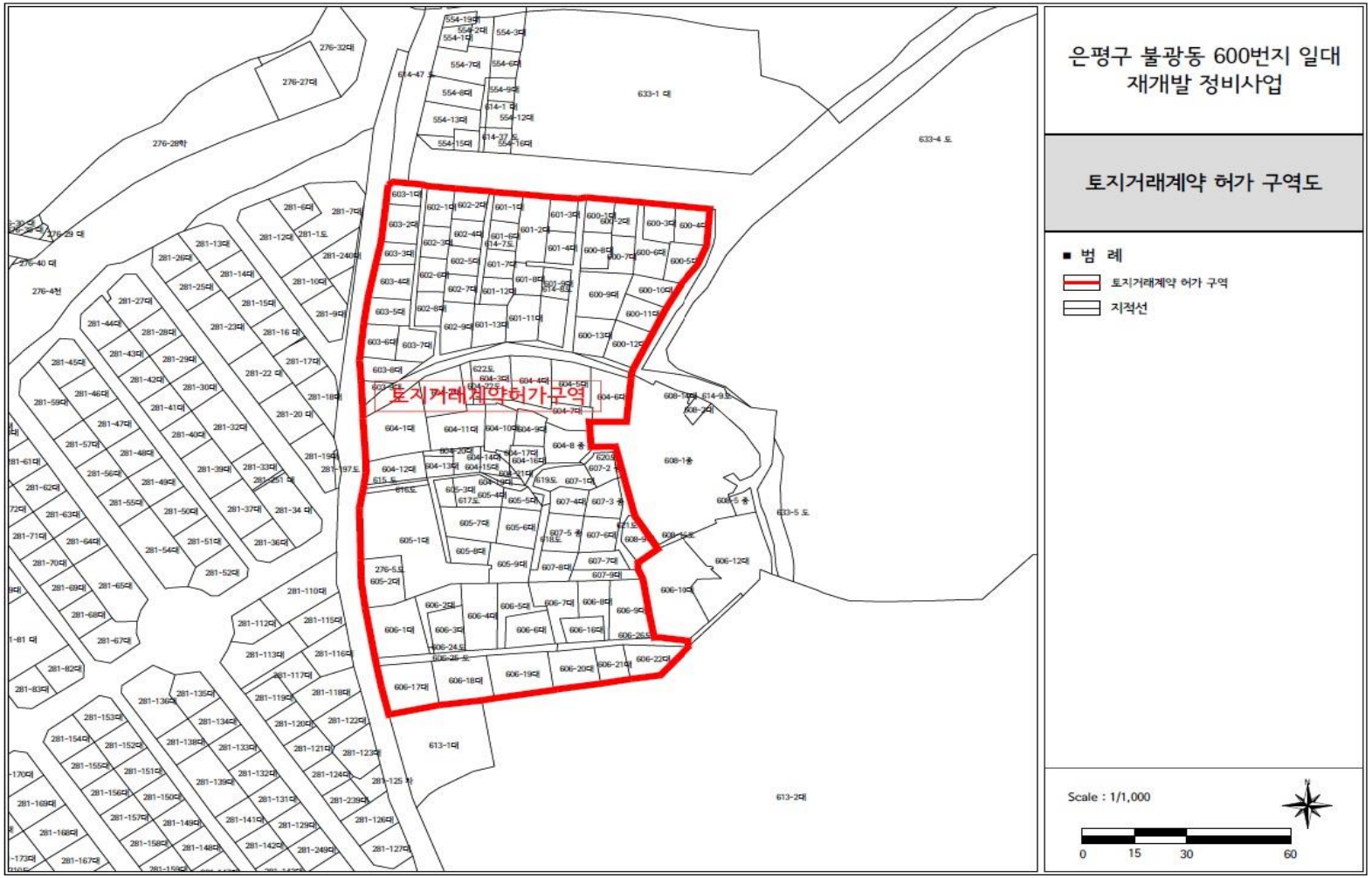

< 서울특별시 서대문구 홍은동 8-400번지 일대 토지거래계약 허가구역 지형도면 >

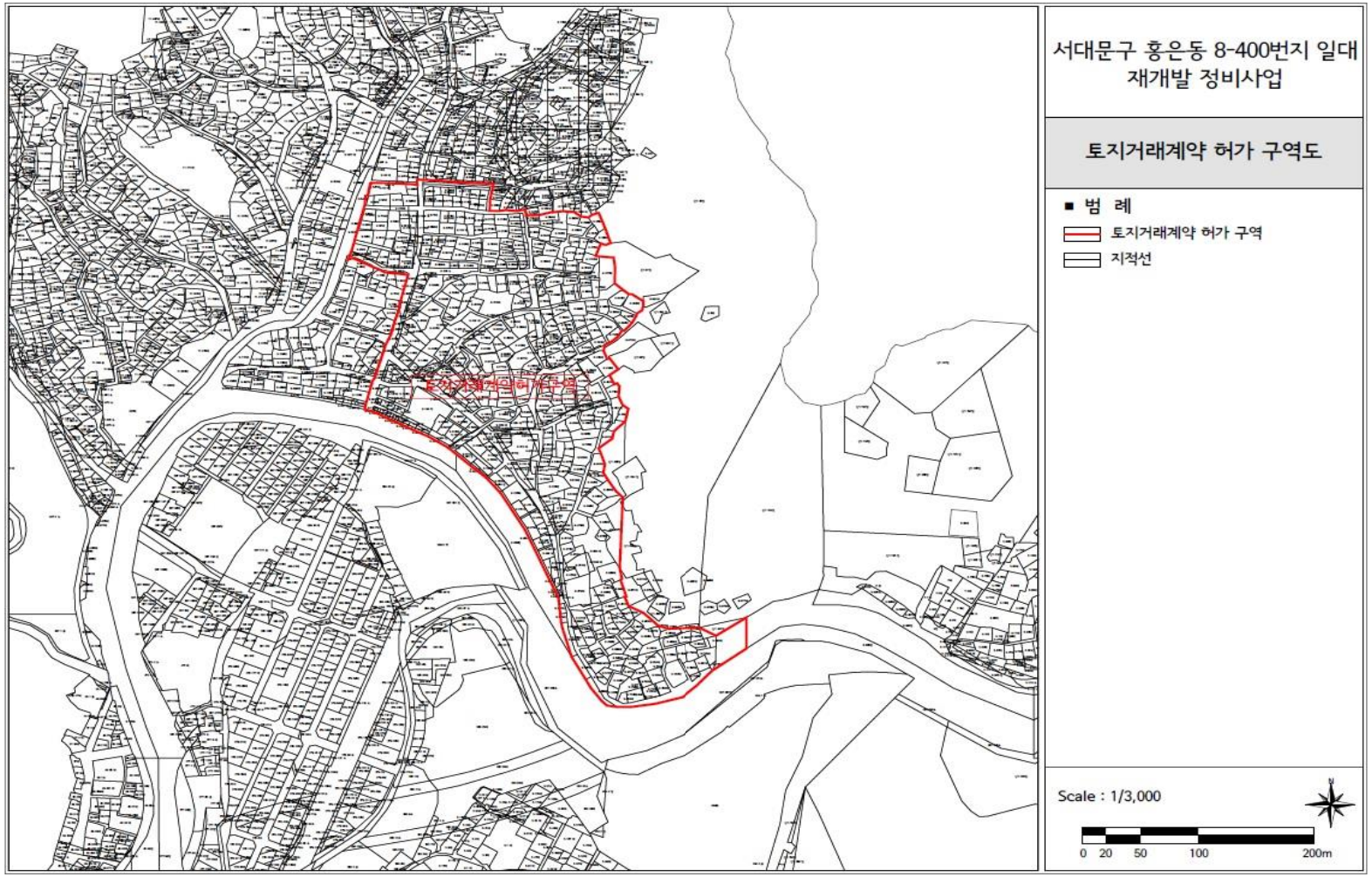

< 서울특별시 마포구 공덕동 11-24번지 일대 토지거래계약 허가구역 지형도면 >

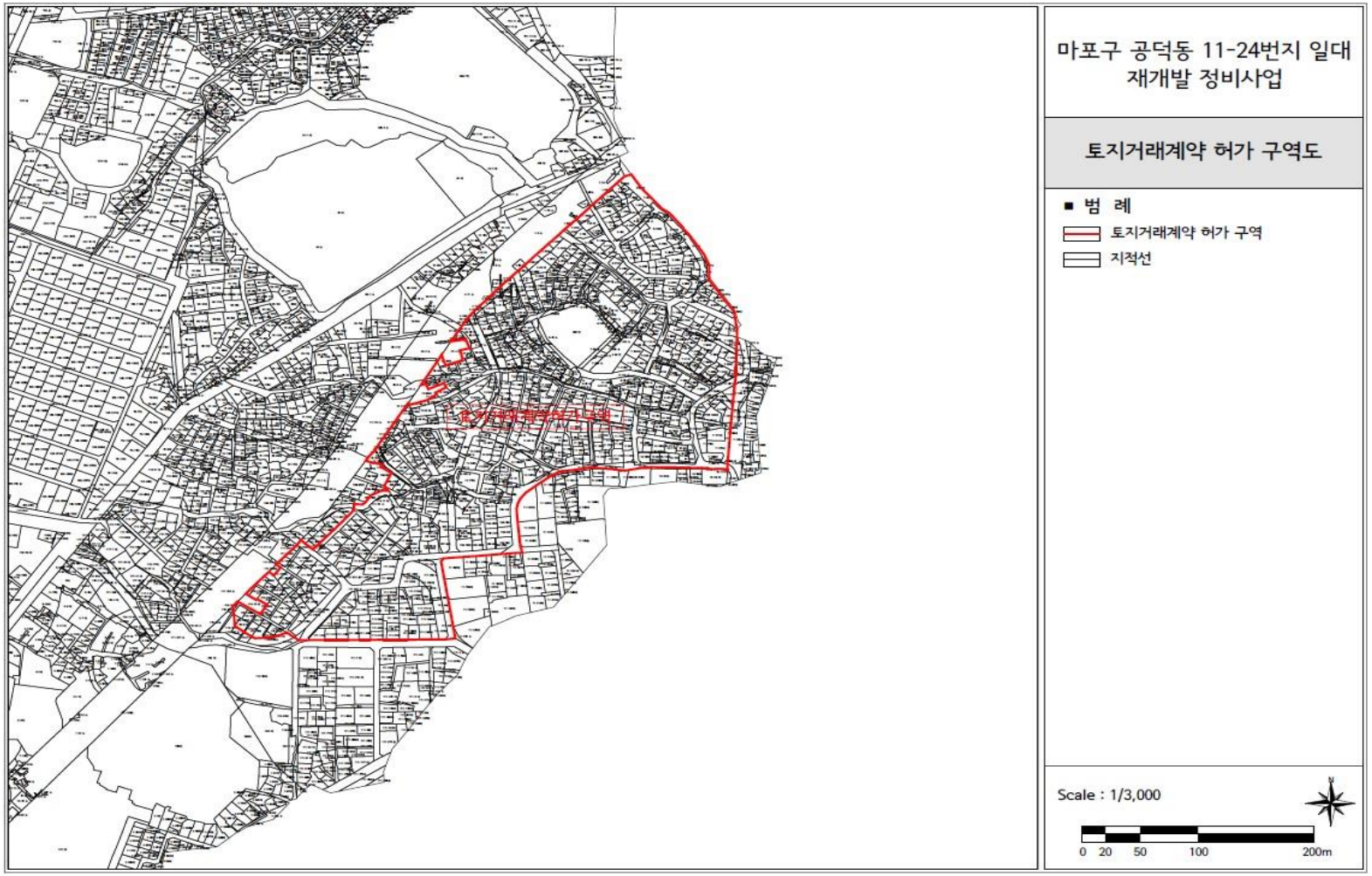

< 서울특별시 양천구 신월7동 913~976번지 일대 토지거래계약 허가구역 지형도면 >

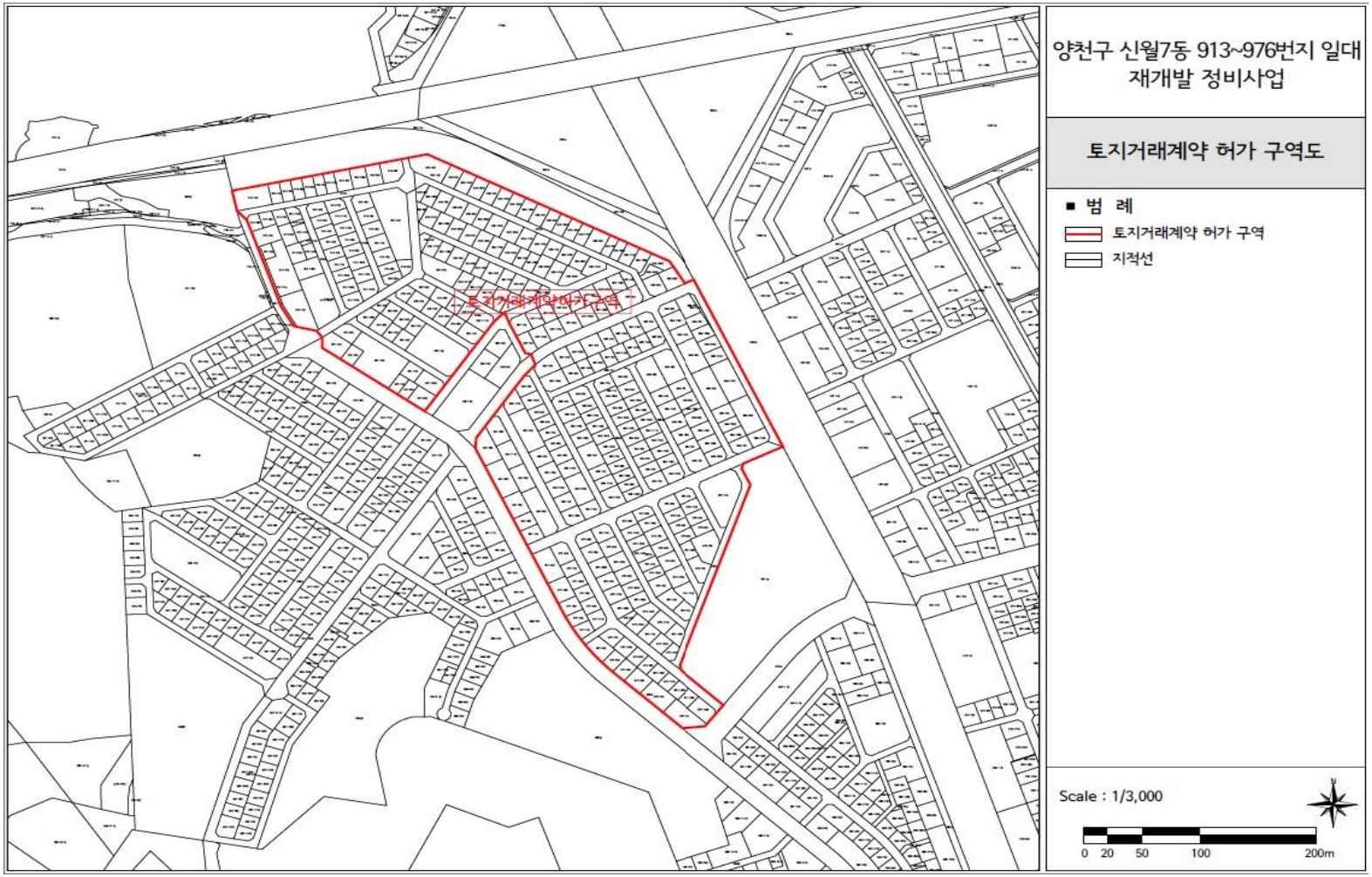

< 서울특별시 강서구 방화동 589-13번지 일대 토지거래계약 허가구역 지형도면 >

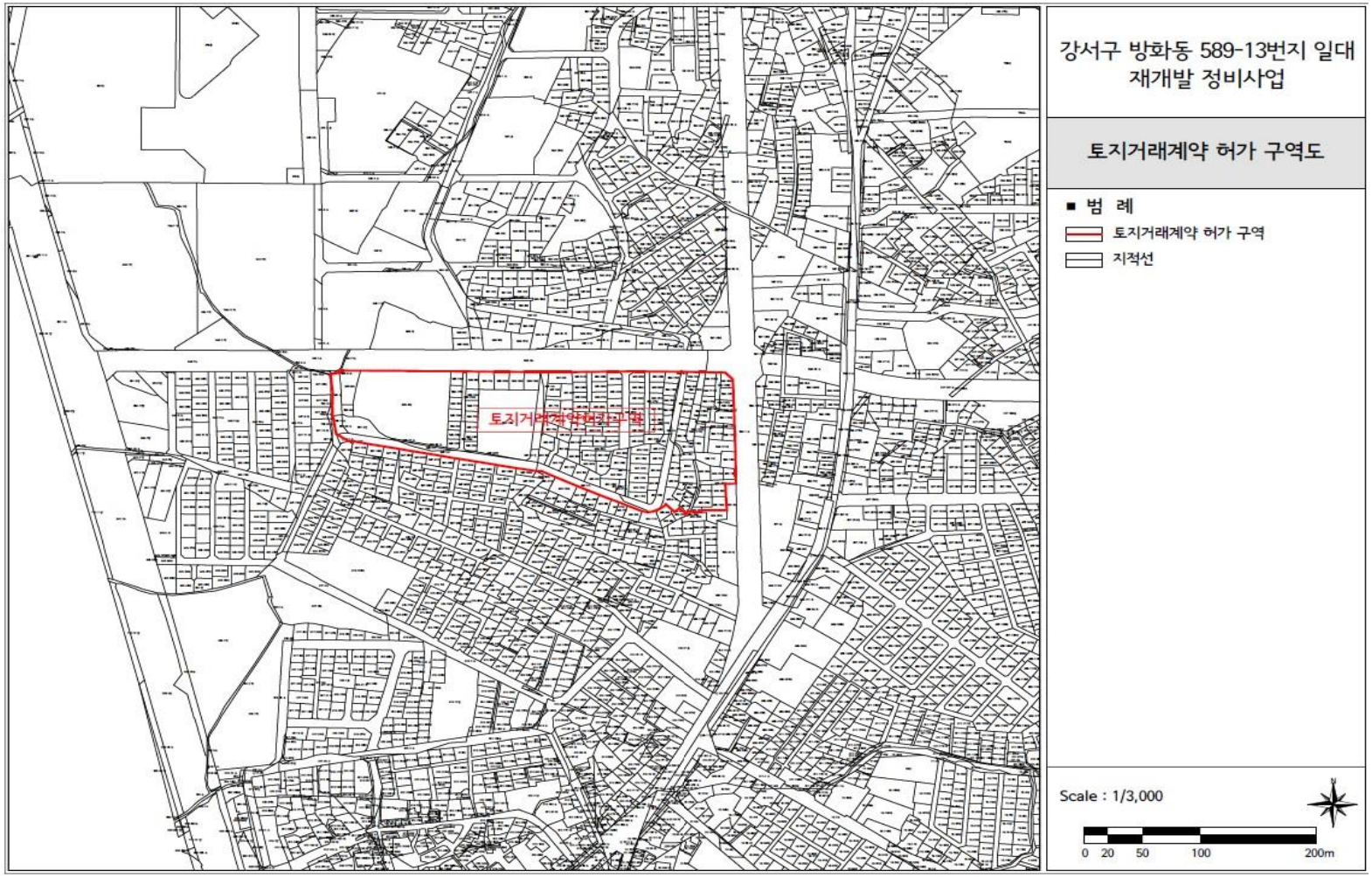

< 서울특별시 구로구 가리봉동 87-177번지 일대 토지거래계약 허가구역 지형도면 >

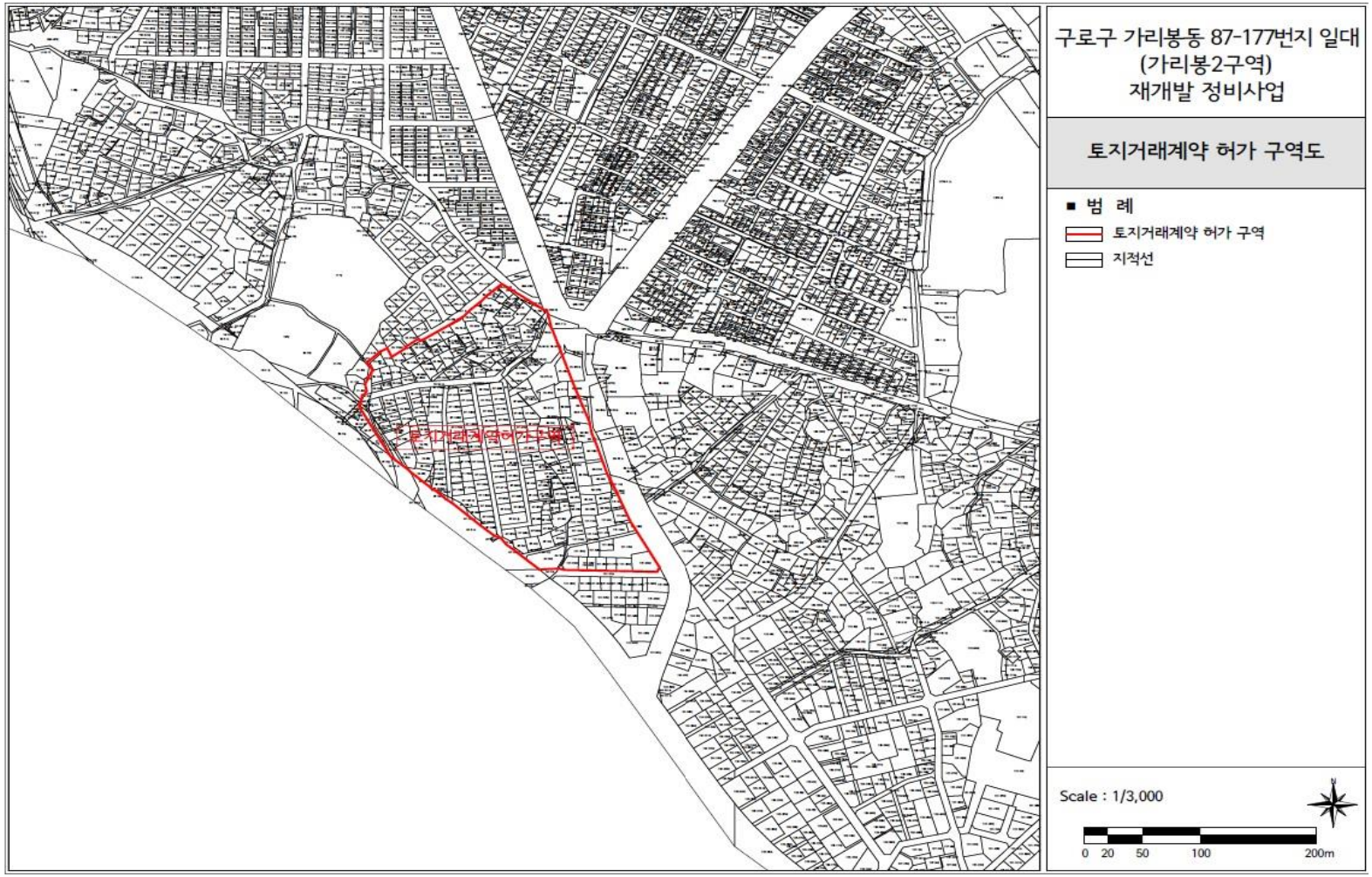

< 서울특별시 금천구 시흥4동 810번지 일대 토지거래계약 허가구역 지형도면 >

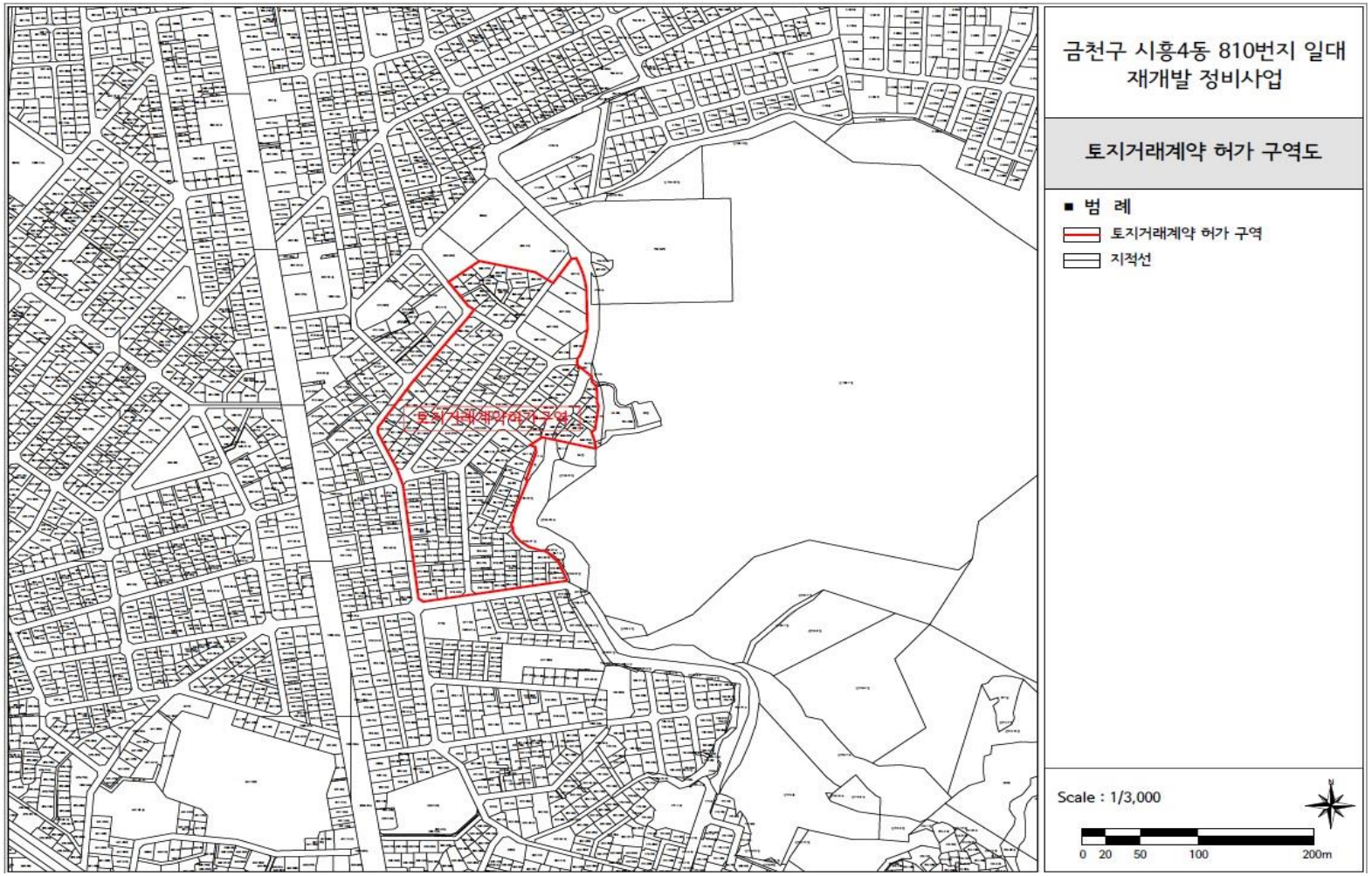

< 서울특별시 영등포구 당산동6가 104번지 일대 토지거래계약 허가구역 지형도면 >

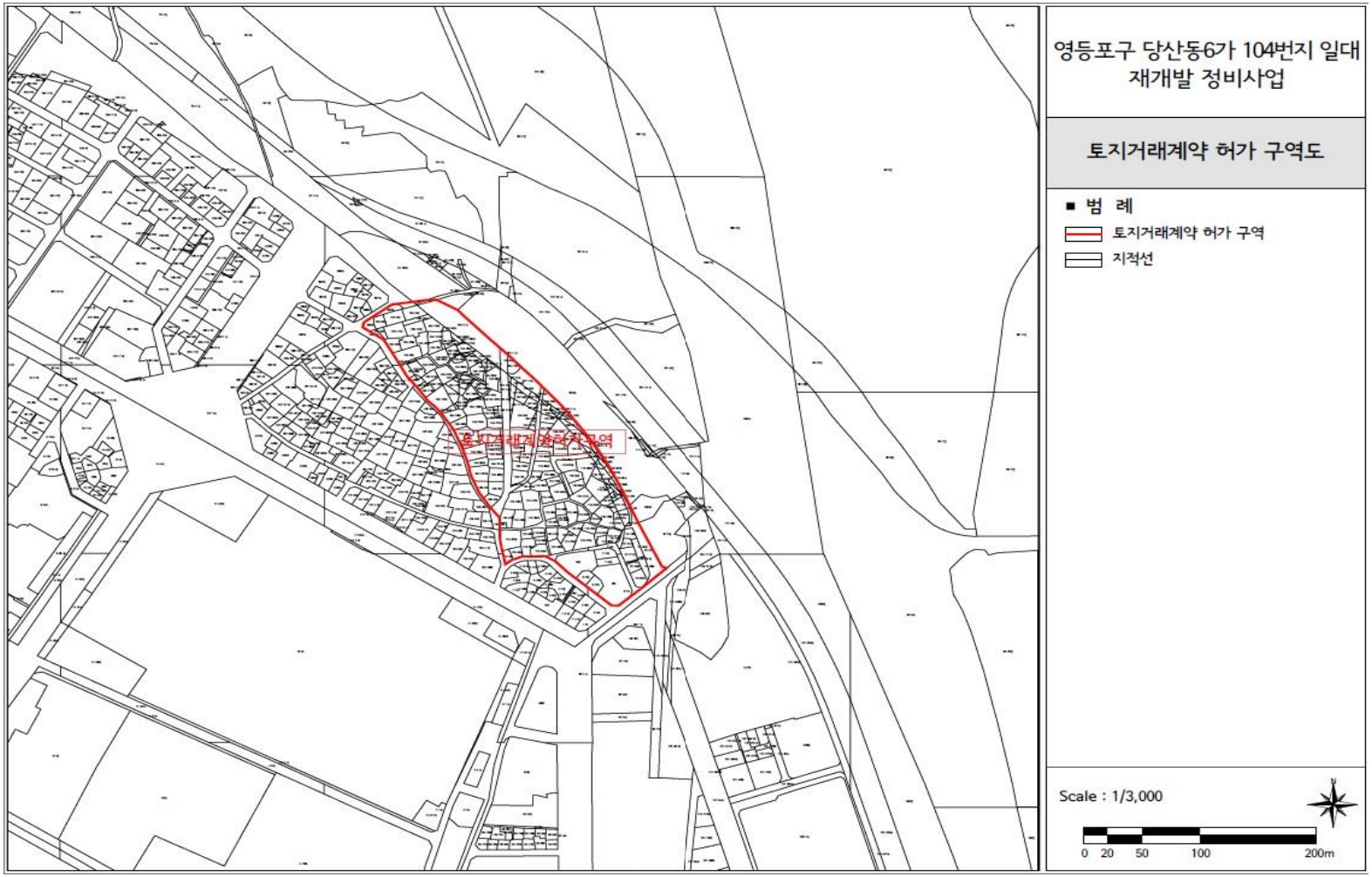

< 서울특별시 동작구 상도동 244번지 일대 토지거래계약 허가구역 지형도면 >

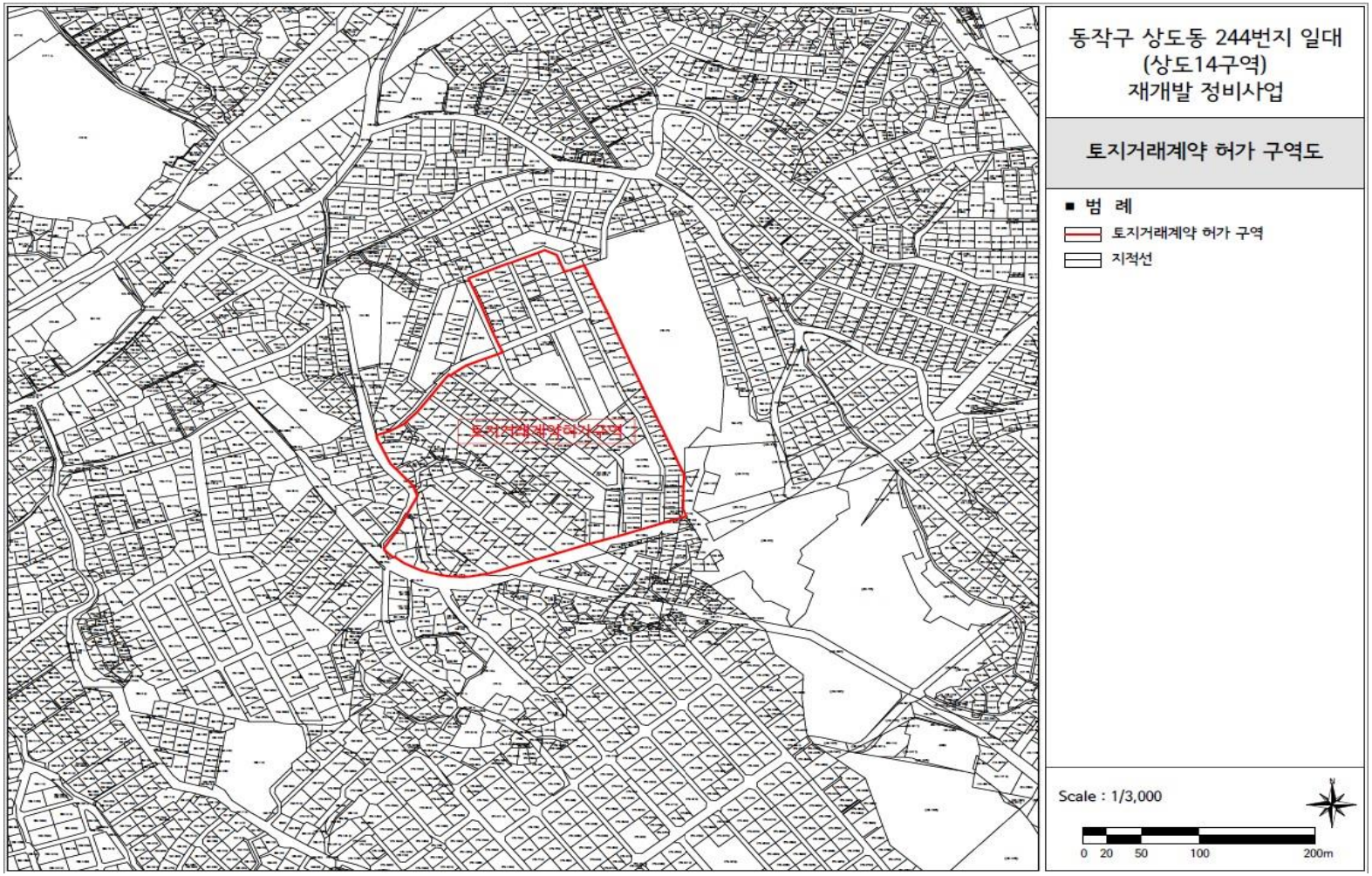

< 서울특별시 관악구 신림동 675-200번지 일대 토지거래계약 허가구역 지형도면 >

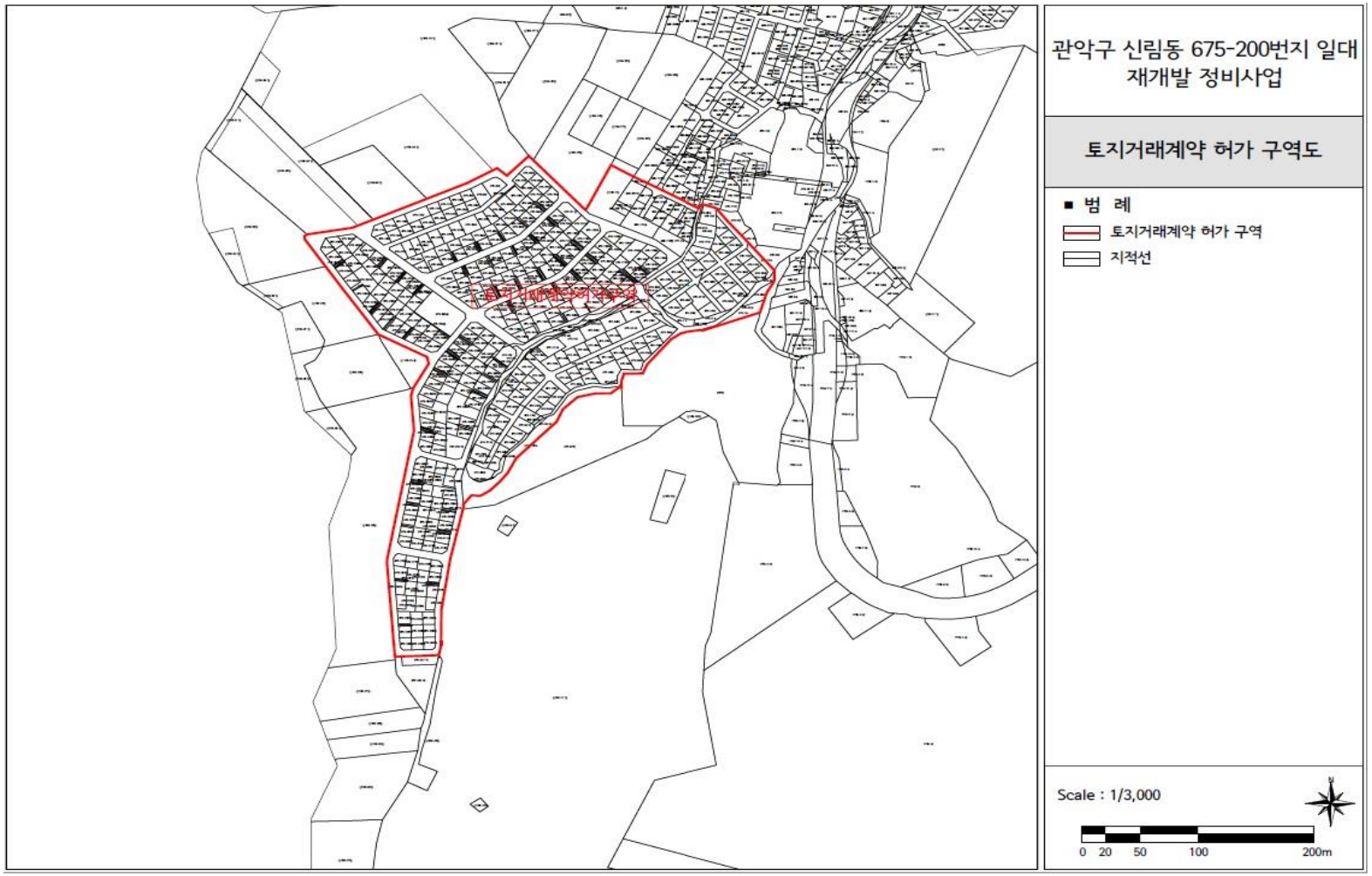

< 서울특별시 송파구 마천동 93-5번지 일대 토지거래계약 허가구역 지형도면 >

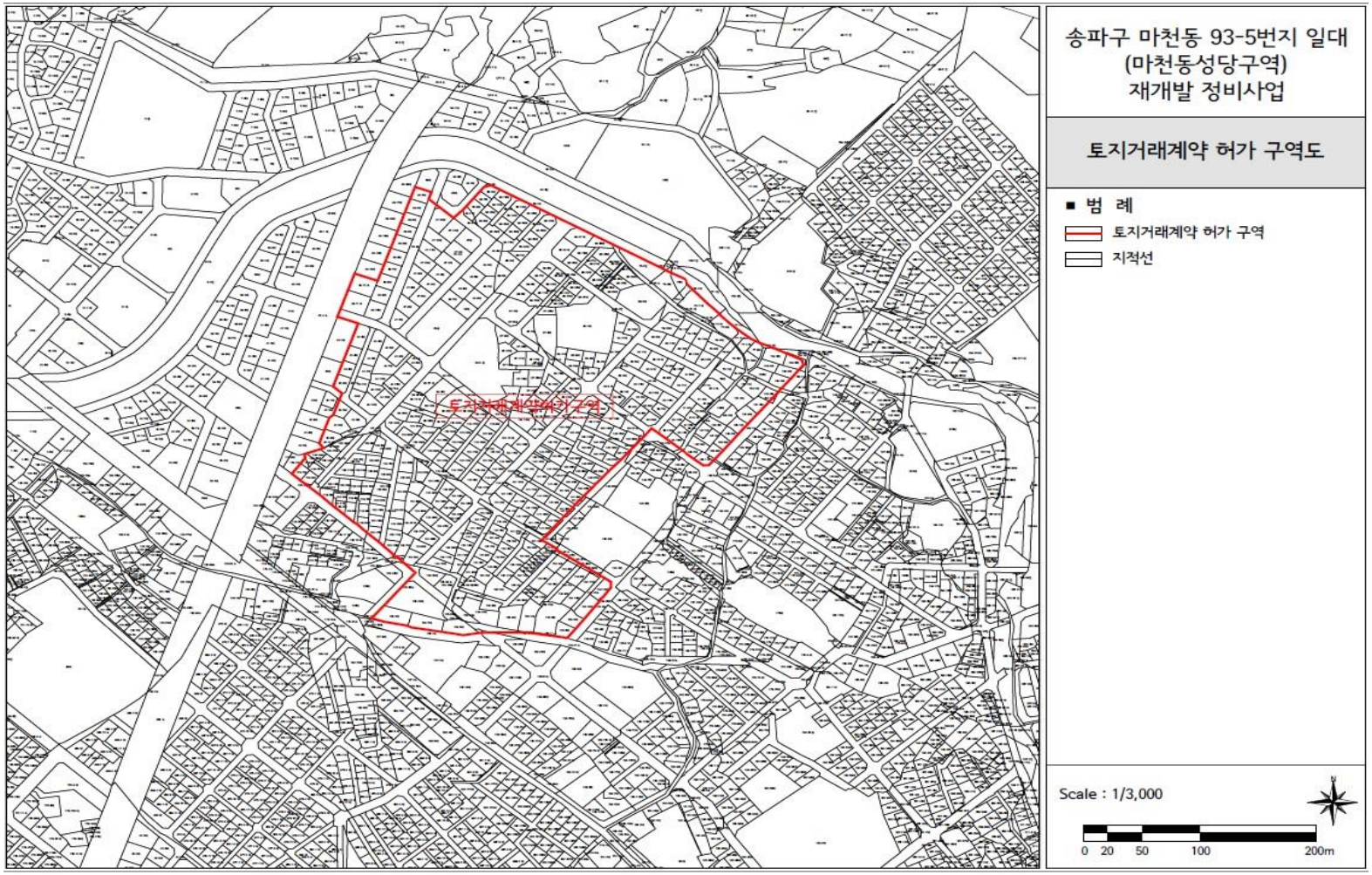
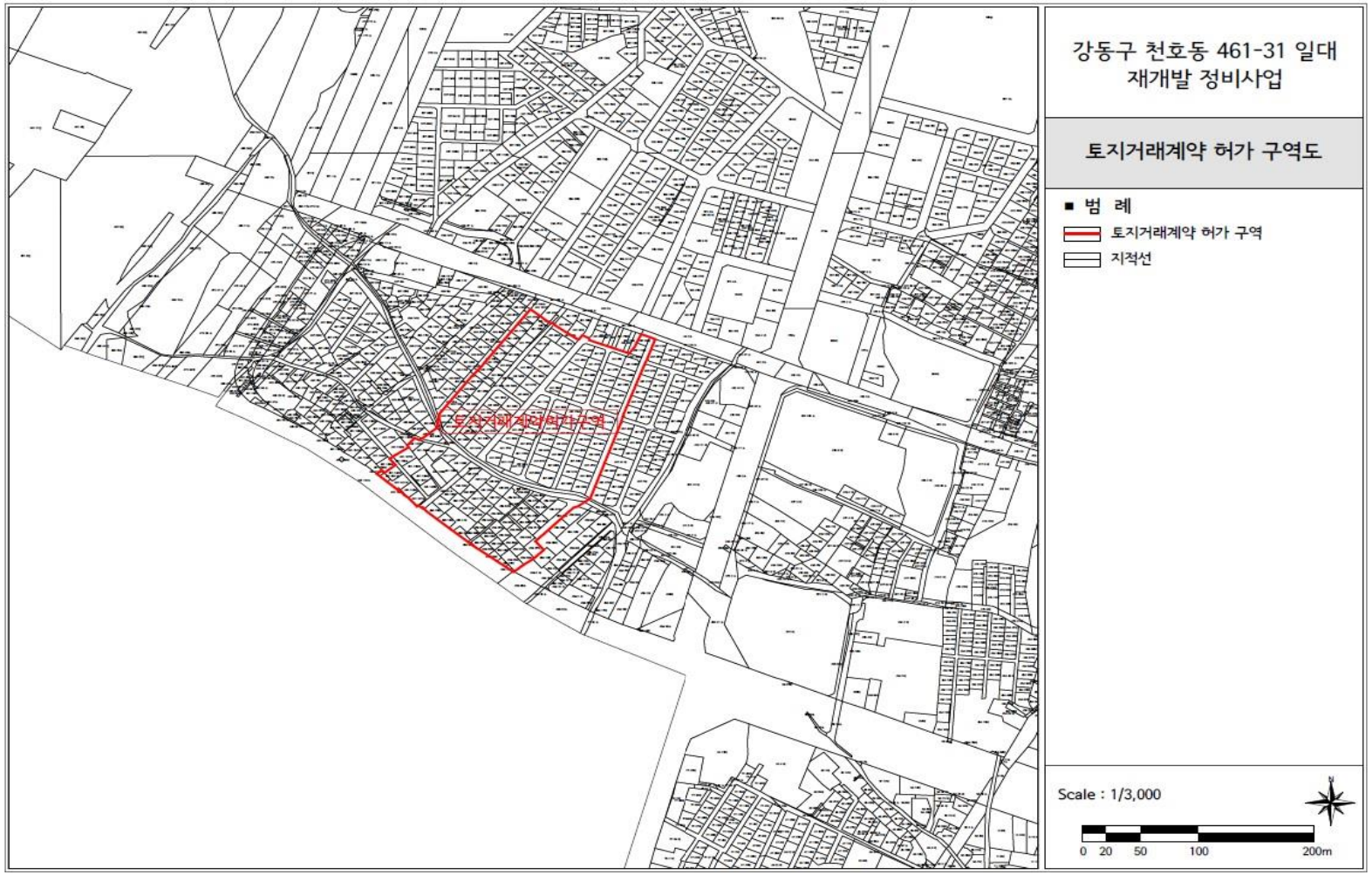
< 서울특별시 강동구 천호동 461-31번지 일대 토지거래계약 허가구역 지형도면 >